SOSTENIBILITÀ E TECONOLOGIE PER LA TRANSIZIONE ECOLOGICA

VDS Sistema Sostenibile

Strategia di controllo premiale applicata ad una fase della nocciocoltura della castanicoltura

VALLE DEL SABATO: il contesto «serinese»

Inquadramento e analisi di contesto territoriale

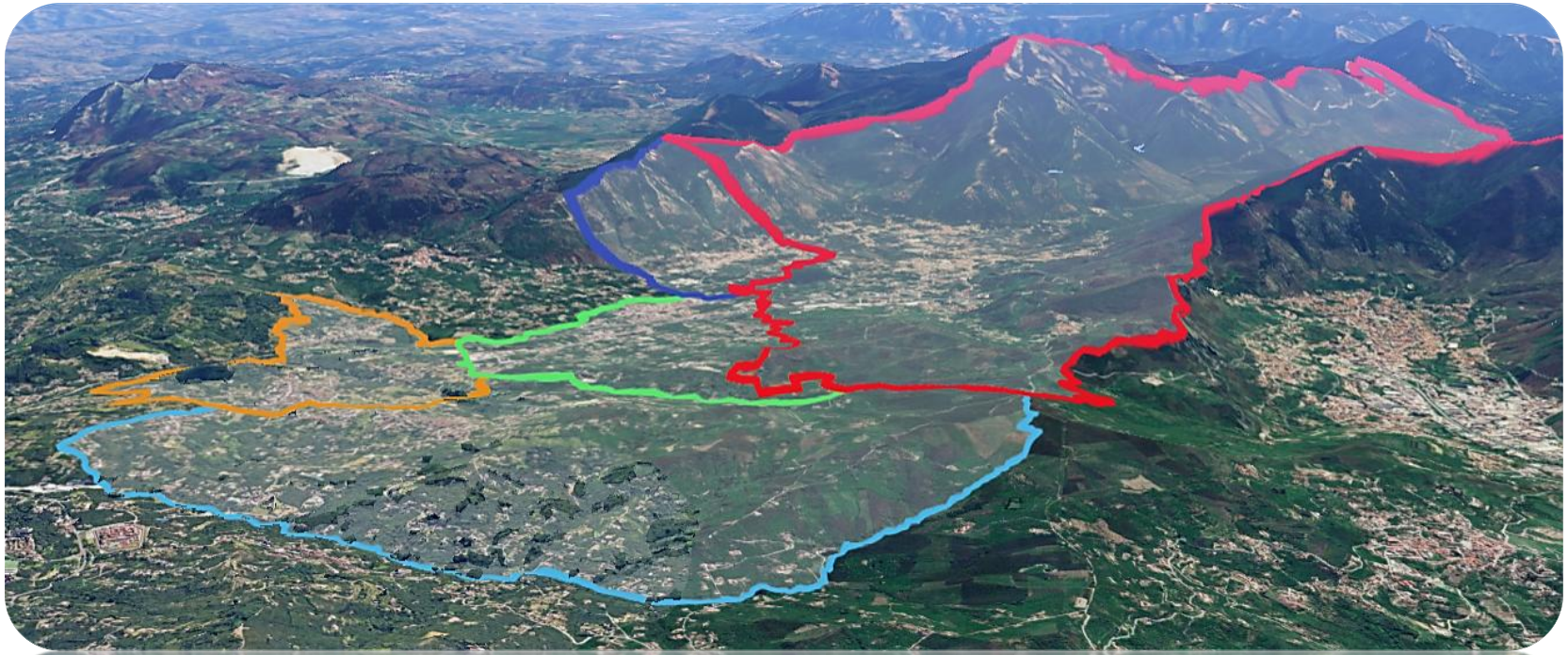

Ortofoto Satellitare Valle del Sabato. Fonte:Google Earth,2025

Dati superficie. Fonte:Istat,2020

Comuni	Superficie territoriale [km²]	Densità abitativa [ab/km²]	Superficie agricola complessiva [%]
Serino	52	127	68
Aiello del sabato	10	371	21
San Michele di Serino	4,47	584	25
Santa Lucia di Serino	3,93	342	80
Cesinali	3,73	676	46

«SUSTINERE»

«NON BASTA PARLARE DI SOSTENIBILITÀ, SERVE COSTRUIRLA PARTENDO DA CIÒ CHE CONOSCIAMO MEGLIO: IL NOSTRO TERRITORIO»

VALLE DEL SABATO: il contesto «serinese»

Inquadramento e analisi di contesto territoriale

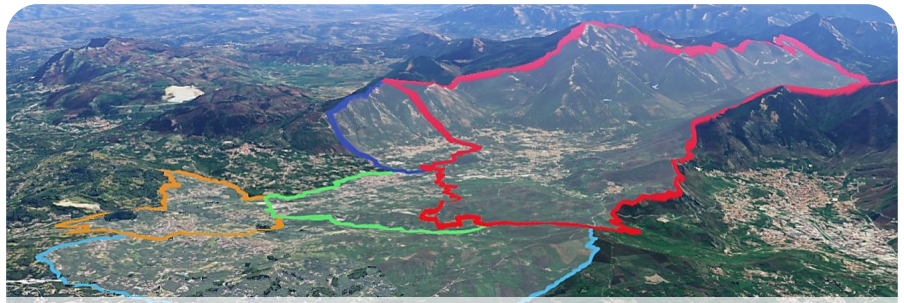

Qual è la tipologia di coltura egemone nel sistema economico di filiera nelSerinese?

Focus sulla **potenzialità produttiva**

Serinese	Provincia di Cuneo
«Marrone di Serino IGP»	«Castagna cuneo IGP»

$$Ip = \frac{N_{aziende\ fruttifere}}{Superficie\ utilizzata} + \frac{Superficie\ colture\ fruttifere}{Superficie\ utilizzata}$$

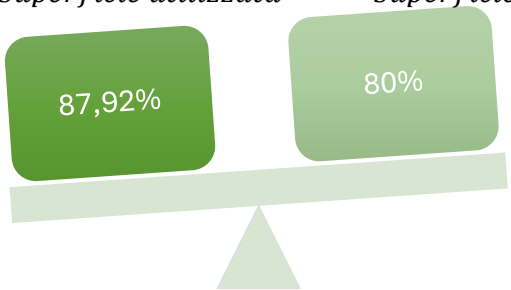

Superficie coltura i-esima/Superficie complessiva utilizzata

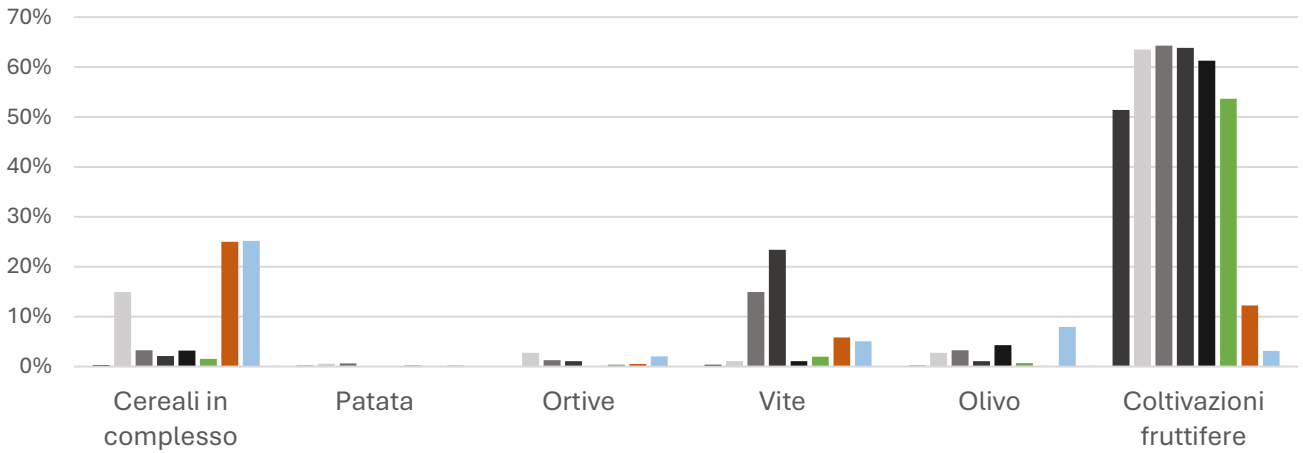

Numero aziende coltura i-esima/Numero aziende complessive

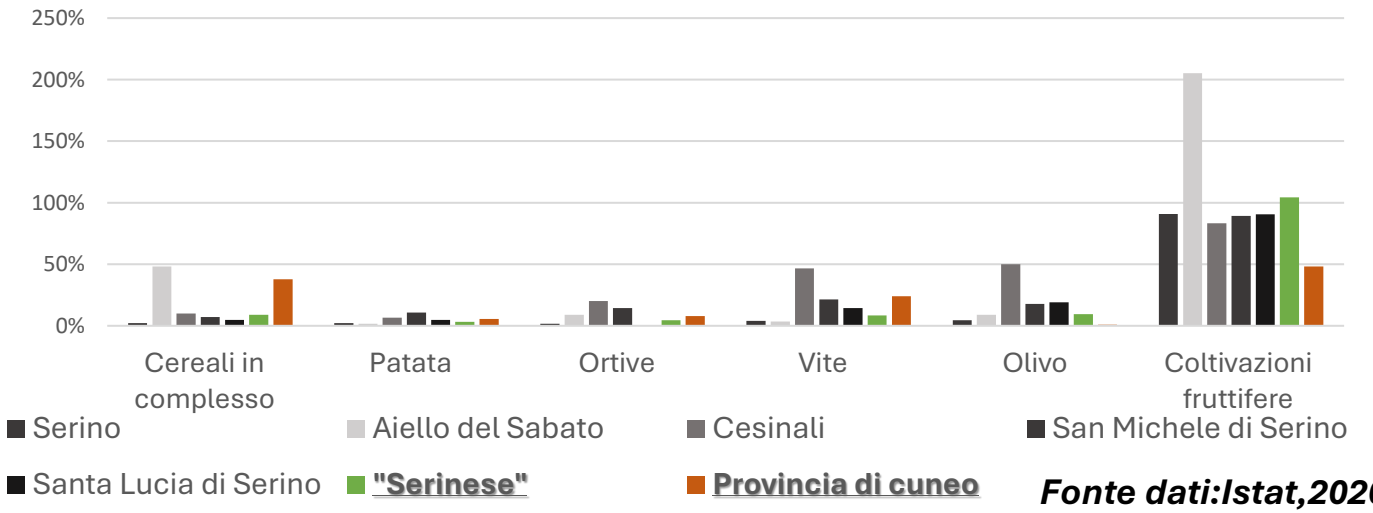

Fonte dati:Istat,2020

INTRODUZIONE AL FENOMENO DI INSOSTENIBILITÀ

Sistema complesso

60.000 quintali/anno

5 milioni di euro

Fonte: Assessorato agricoltura, Regione Campania

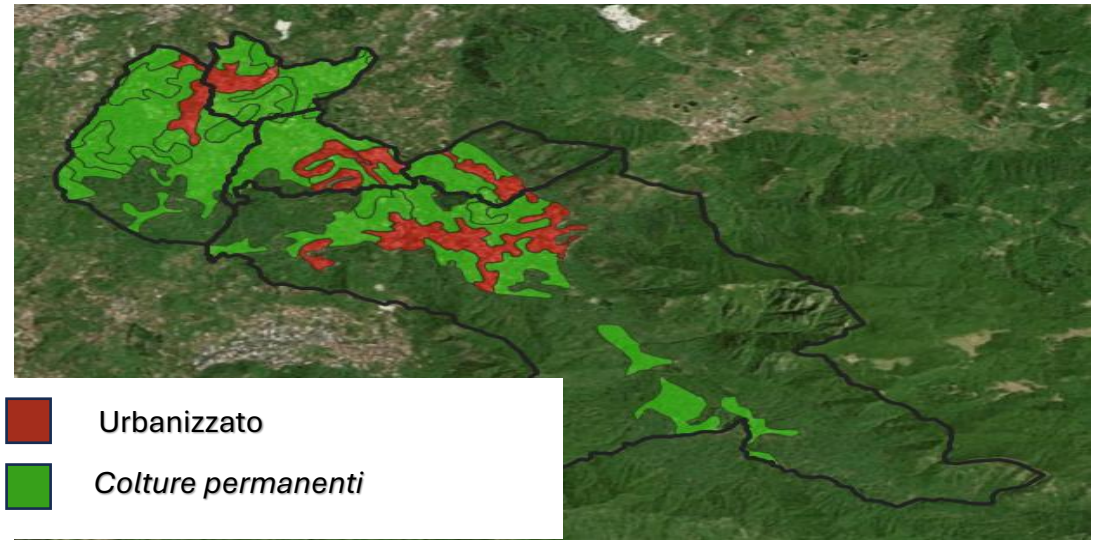

Fonte: Corine Land Cover 2018



«QUI COLTIVIAMO E QUI RESPIRIAMO»

INTRODUZIONE AL FENOMENO DI INSOSTENIBILITÀ

Valutazione della sensibilità territoriale – Segnalazioni 2022



Rete «Aura»

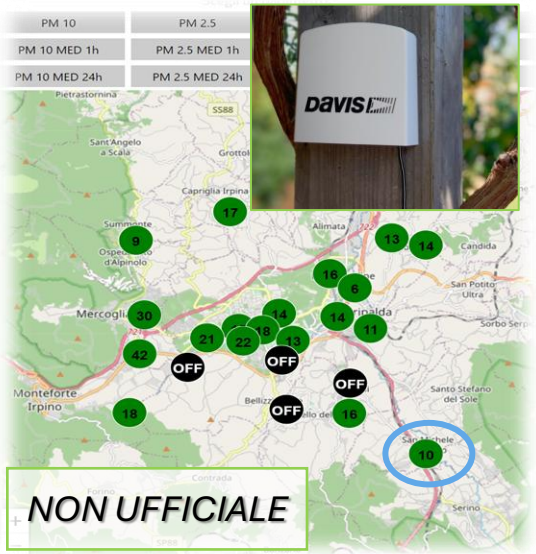

Monitoraggio PM10 – Marzo 2022/Marzo 2023

POPOLAZIONE

Legambiente Alta Valle del Sabato ···
44 min ·

🚨🚨🚨 Come Legambiente chiediamo alle amministrazioni comunali un'azione comune contro gli abbruciamenti agricoli innanzitutto con delle ordinanze coerenti e coordinate tra i vari paesi della Valle del Sabato perché i fumi purtroppo non rispettano i confini territoriali, ma ancora di più, chiediamo una soluzione immediata che possa mettere la parola fine a questa pratica che rende la nostra aria irrespirabile, offrendo ai cittadini alternative per lo smaltimento di sfalci e ramaglie. #cisiamorottipolmoni #noagliabbruciamentiagricoli Comune di San Michele di Serino Comune di Serino Comune di Santo Stefano del Sole Comune di Cesinali Comune Di Aiello Del Sabato (Av) Comune di Santa Lucia di Serino

ISTITUZIONI

Comune di Aiello del Sabato
Provincia di Avellino

SETTIMANA	COMUNE DI AIELLO DEL SABATO
dal 28 febbraio al 06 marzo 2022	ABBRUCIAMENTI CONSENTITI IL MARTEDI' E GIOVEDI' DALLE ORE 11:00 ALLE 16:00
dal 07 al 13 marzo 2022	DIVIETO DI ABBRUCIAMENTI PER TUTTA LA SETTIMANA
dal 14 al 20 marzo 2022	ABBRUCIAMENTI CONSENTITI IL MARTEDI' E GIOVEDI' DALLE ORE 11:00 ALLE 16:00
dal 21 al 27 marzo 2022	DIVIETO DI ABBRUCIAMENTI PER TUTTA LA SETTIMANA
dal 28 marzo al 03 aprile 2022	ABBRUCIAMENTI CONSENTITI IL MARTEDI' E GIOVEDI' DALLE ORE 11:00 ALLE 16:00
dal 04 al 10 aprile 2022	DIVIETO DI ABBRUCIAMENTI PER TUTTA LA SETTIMANA
dal 11 al 17 aprile 2022	ABBRUCIAMENTI CONSENTITI IL MARTEDI' E GIOVEDI' DALLE ORE 11:00 ALLE 16:00

EFFETTI

Residui vegetali bruciati tra Serino e San Michele, 7 denunciati

Indagine dei Carabinieri della Compagnia di Solofra. Gli indagati hanno età compresa tra i 26 e 70 anni

Di **Redazione** - 14 Novembre 2024

Bruciava sterpaglie poco distante dalle case, nei guai una donna di Aiello del Sabato

Cronaca

INTRODUZIONE AL FENOMENO DI INSOSTENIBILITÀ

Modello DPSIR. Che azione intendiamo realizzare?

Relazione causale:

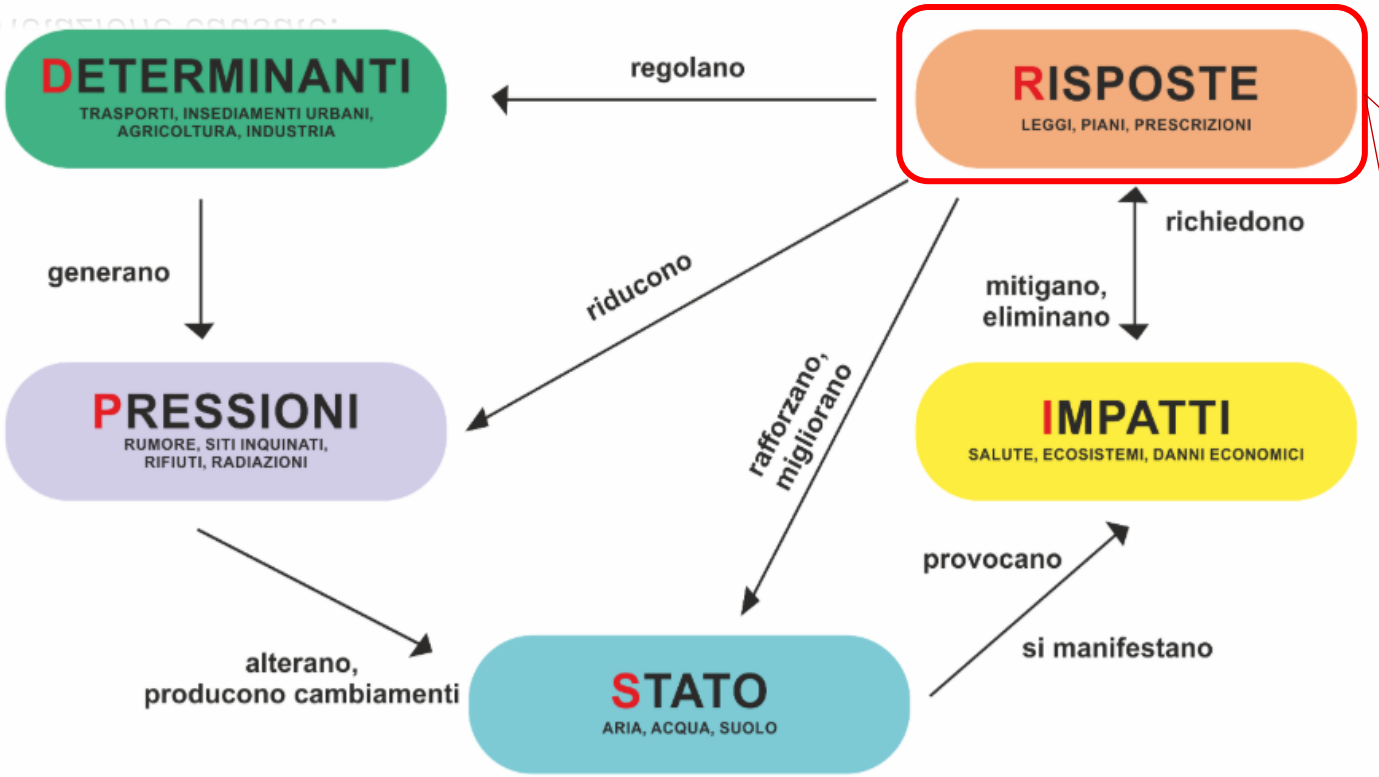

Fonte: EEA

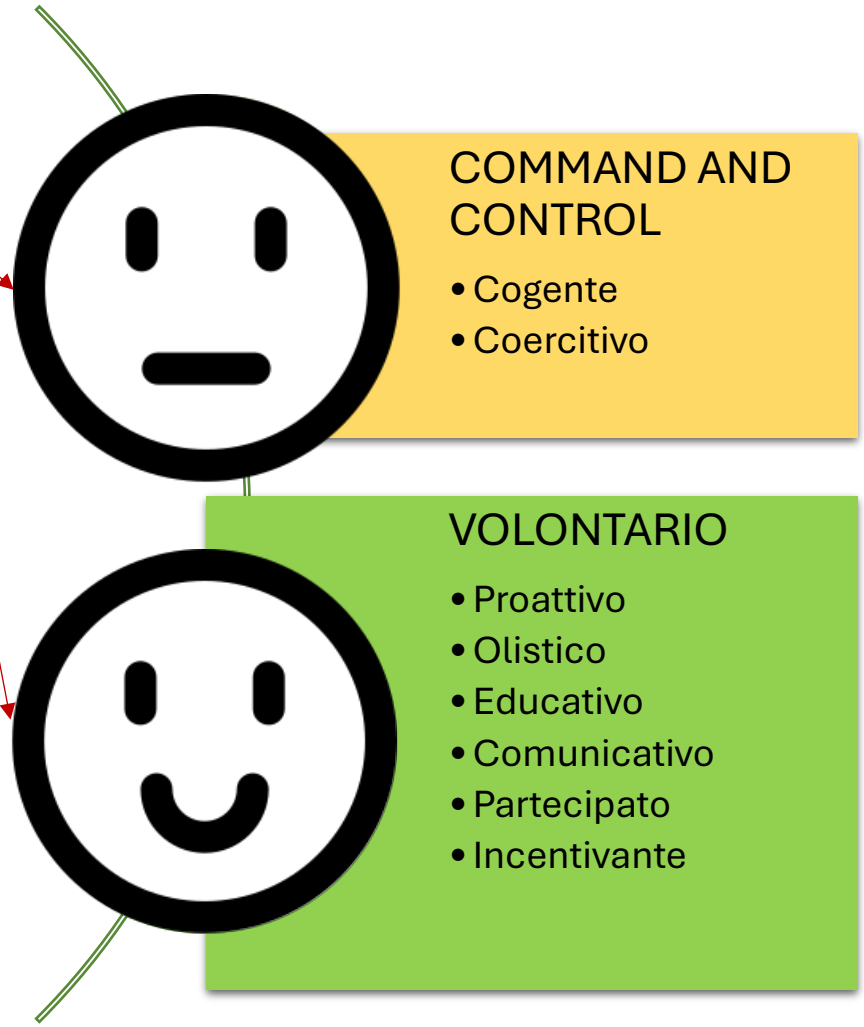

STRATEGIA DI CONTROLLO DI UN ASPETTO AMBIENTALE

Flusso logico del sistema intercomunale, chiuso e interno

Proattivo | Olistico | Educativo | Comunicativo | Trasparente | Integrato

Soggetto proponente

Analisi Aspetto ambientale

ELAB. DOCUMENTAZIONE
- Politica e programma ambientale
- Procedure di gestione
- Modalità operative
- Moduli

FUNZIONE
- **Economica**
  Finanziamento del sistema premiale
- **Amministrativa**
  Gestione delle adesioni volontarie
- **Coordinamento**
  Supporto alla comunicazione e alla formazione

STAKEHOLDERS e CITTADINI

STAKEHOLDERS e CITTADINI
Obiettivi e traguardi

Formazione

PLAN
DO
CHECK
ACT

STRUMENTO DI ATTUAZIONE

PORTALE VDS SOSTENIBILE

Adozione dei requisiti aggiornati documentandoli

Adesione volontaria o rinnovo annuale dell'idoneità

Proprietario, detentore o locatario

IGP Castagna di Serino

Consorzio di tutela

Audit

Conformità urbanistico catastale
Conformità amministrativa
Conformità operativa

Validazione e proporzionamento premialità

VDS CARD

Riscossione

PIANIFICAZIONE DELLA STRATEGIA DI CONTROLLO

Analisi del processo e individuazione dell'aspetto ambientale significativo

Attività

Preparazione del terreno

Fasi elementari
- Aratura
- Concimazione
- Livellamento
- Irrigazione pre-semina
- Residui e scarti

Piantumazione
- Semina manuale o meccanizzata
- Periodo di semina (stagionalità)
- Residui e scarti

Crescita e sviluppo
- Irrigazione regolare
- Trattamenti fitosanitari e fertil. (diserbo, antiparassitari)
- Monitoraggio
- Residui e scarti

Raccolta
- Manuale o meccanizzata
- Tecniche di raccolta selettiva (per qualità)
- Residui e scarti

Gestione post-raccolta
- Smistamento / selezione del prodotto
- Stoccaggio
- Essiccazione (se necessaria)
- Residui e scarti

Potenziali impatti connessi agli aspetti

AAS

Combustione
Punti di incenerimento diffusi e incontrollati

POTENZIALI IMPATTI SIGN.

- Suolo
- Atmosfera
  Potenzialmente significativo (slide 6)

Fonte: Servizio Fitosanitario Regione Toscana

PIANIFICAZIONE DELLA STRATEGIA DI CONTROLLO

Programma ambientale e alternative di gestione

Proattivo | Olistico | Educativo | Comunicativo | Trasparente | Integrato

3 A

Obiettivi da perseguire	Traguardi e indicatori	Strumenti
Mantenimento e tutela della Q.A.	Riduzione del **70%** delle emissioni complessive da gestione dei residui agricoli ed incendi e controllo dei potenziali combustibili	Premialità per la gestione residuale virtuosa
		Premialità prevenzione del rischio incendi
Tutela della composizione dei suoli		Premialità per la selezione degli imballaggi
Partecipazione e coinvolgimento attivo alla politica ambientale	Adesioni per oltre il 60% delle aziende censite nel campo di applicazione.	Portale VDS Sostenibile

L'articolo 185, comma 1) del D.Lgs. 152/06 e s.m.i. prevede che siano **escluse dalla disciplina sui rifiuti** (parte l[illegible]enti tipologie di materiali:

- le materie fecali, paglia, sfa[illegible]tatur[illegible]nonché altro materiale agricolo o forestale naturale non [illegible]ric[illegible]o **[illegible]tilizzati in agricoltura**, nella selvicoltura **o per la produ[illegible]ne d[illegible]rgia** da tale biomassa mediante processi o metodi che non da[illegible]o l'ambiente né mettono in pericolo la salute umana, anche con **eventuale cessione a terzi**

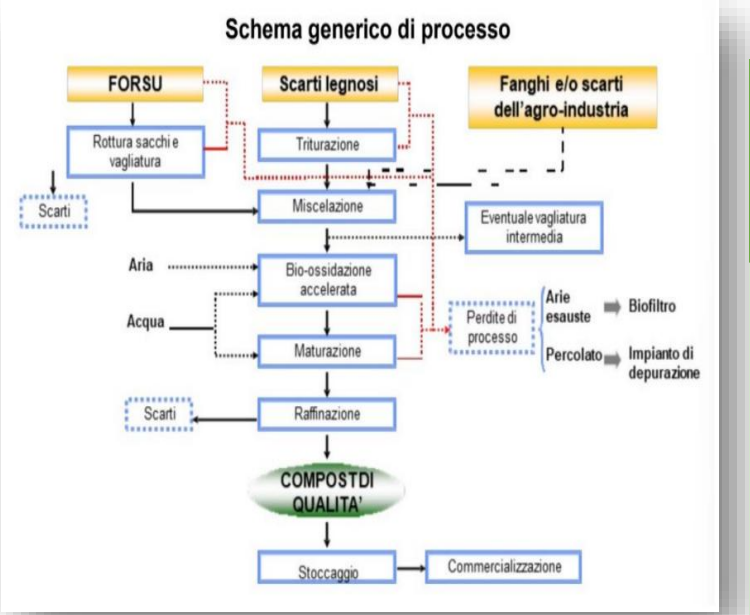

CONFERIMENTO AD IMPIANTI AUTORIZZATI (3)

- Classificazione di rifiuto speciale non pericoloso CER 20.02.01
- Garantire la tracciabilità con eventuali deroghe
- Coadiuvante al processo di recupero di materia e produzione di compost di qualità
- Audit

PIANIFICAZIONE DELLA STRATEGIA DI CONTROLLO

Meccanismo di attribuzione del credito sostenibile

Proporzionamento del credito sostenibile → Aliquota fissa + Aliquota variabile =

Obiettivo integrato:
Lotta comunitaria all'insetto Cinipide → Fitosanitari ecocompatibili

ALIQUOTA FISSA

Fasce di attribuzione	Percentuale incombusta autodichiarata*	Premialità	Fabbisogno stimato
A	95%-100%	90% f.s.	L.D. A/B/C/D
B	80%-95%	80% f.s	L.D. A/B/C/D
C	65%-80%	70% f.s.	L.D. A/B/C/D
D	50%-65%	50% f.s.	A/B/C/D

***Per il calcolo delle percentuali formare dei cumuli di materiale di dimensioni confrontabili e H = 70 cm e adottare questa formula:** $\frac{\textit{Numero di cumuli indirizzati a combustione}}{\textit{Numero di cumuli complessivi}} * 100$

*Reintegro nutritivo addizionale per asportazione di frutti, foglie e rami (**azoto, anidride fosforica, potassio e calcio**) → Biofertilizzante*

ALIQUOTA VARIABILE — FASCIA A

Aree tematiche	Categorie	Criteri
1.Emissioni da trattamento	1.1 Imballaggi	1.1.1 Riduzione materiale
		1.1.2 Imballaggi biodegradabili certificati
	1.2 Gestione dei residui	1.2.1 Movimentazione off-site
		1.2.2 Movimentazione on-site
		1.2.3 Biocompatibilità pregressa
2.Sicurezza territoriale	2.1 Prevenzione rischio incendi	2.1.1 Fasce tagliafuoco
		2.1.2 Tempestività di gestione residuale

PIANIFICAZIONE DELLA STRATEGIA DI CONTROLLO

Procedura di valutazione – Aliquota variabile

Criterio	Esigenza	Indicatore	Unità di Misura	Scala di Prestazione	Metodo di Misura	Peso
1.1.1. Riduzione materiale	**Prevenire la gestione impropria di rifiuti da imballaggio**	% di riduzione rispetto allo standard aziendale	%	0–5% = 5 / 5–15% = 10 / >15% = 15	Analisi documentale acquisti rispetto all'anno precedente	10%
1.1.2 Imballaggi biodegradabili certificati	**Favorire l'ottica di economia circolare**	% di imballaggi certificati rispetto al totale	%	0–30% = 5 / 30–70% = 10/ >70% = 15	Verifica certificati di fornitura e composizione	10%
1.2.1 Movimentazione off-site	**Controllare le emissioni da trasporto**	Distanza dalla sede di conferimento	km	>15= 8 / 15-5= 15 / <5 = 18	Verifica formulari, DDT, convenzioni con impianti	20%
1.2.2 Gestione on-site	**Favorire sorgenti a bassa emissione per alimentazione delle attrezzature**	Manuale o % di elettrico su comb.fossili	%	Tot. Manuale =22 <30 = 10 / 30–70 = 15/ >70 = 20	Report tecnico + sopralluogo	25%
1.2.3 Biocompatibilità pregressa	**Premiare pratiche virtuose di trattamenti fitosanitari biologici**	Anni di adesione a pratiche certificate	Anni	<2 = 5 / 2–5 = 10 / >5 = 15	Registro storico partecipazione e rendicontazioni precedenti	10%
2.1.1 Fasce tagliafuoco	**Prevenire la propagazione di incendi mediante la creazione di fasce tagliafuoco**	Lunghezza e continuità delle fasce realizzate	m	<50m = 5 / 50–150m =10/ >150m = 15	Sopralluogo, georeferenziazione, foto documentali	15%
2.1.2 Tempestività di gestione residuale	**Evitare l'accumulo prolungato di biomasse combustibili**	Tempo tra raccolta e smaltimento residuo	Giorni	>30 = 5 / 15–30 = 10 / <15 = 15	Registro temporale lavorazioni/smaltimento	15%

PIANIFICAZIONE DELLA STRATEGIA DI CONTROLLO

Procedura di attribuzione complessiva

Punteggio Totale AT1+ AT2 (pt)	Livello	Aliquota Premiale di Spettanza
0–29	Non Conforme	0% f.s.
30–49	Base	40% f.s.
50-69	Intermedio	60% f.s.
70–99	Avanzato	80% f.s.
≥ 100	Eccellente	100% f.s.

VDS SOSTENIBILE

Castagna di Serino

Certificato Verde Elettronico

Riconoscimento dei crediti di sostenibilità

Il presente certificato attesta la conformità dell'azienda alla procedura volontaria di gestione sostenibile dei residui agricoli. I benefici connessi alla maturazione del credito di sostenibilità e riportati di seguito **saranno proporzionati in funzione del fabbisogno stimato e accreditati direttamente sul profilo del beneficiario connesso alla VDS Card in dotazione.** La carta rappresenta l'unico titolo da esibire all'esercente per provvedere al ritiro, nel punto di vendita fisico, della merce di spettanza.

Informazioni

Nome persona giuridica	Azienda Agricola Marrone
Identificativo procedurale	AAM-VDS
Codice Fiscale / P.IVA	13542581
Sito di riferimento	ID: AAM-01| Foglio 15, Particella 88, Sub 3
Procedura di riferimento	DISC-VDS/PDCA-01_Rn.25/05
Validità	Annuale – soggetta a rinnovo
Codice ritiro biofertilizzante	VDSAAM03

Esito della valutazione per l'attribuzione premiale

Aliquota fissa – Fitosanitari ecocompatibili

Percentuale incombusta	Livello raggiunto	Livello di danno stimato
95-100%	100% fabbisogno stimato	B

Aliquota variabile - Biofertilizzante

Area Tematica	Punteggio Ottenuto	Livello	
1 – Emissioni	78 / 85	-	
2 – Sicurezza	25 / 30	-	
Totale	103 / 115	Eccellente	

STRUMENTI DI ATTUAZIONE DELLA STRATEGIA

Portale Web: VDS Sostenibile

INFORMATIVO

EDUCATIVO E COMUNICATIVO

AMMINISTRATIVO

VDS Sostenibile